Análisis Exploratorio de Datos: Suicidios en Colombia (2021)

Samuel Gómez & Jacobo Petelli

Introducción

Este documento presenta un análisis exploratorio de datos (EDA) sobre los incidentes de intentos de suicidio y suicidios registrados en Colombia durante el año 2021. Los datos incluyen información por semana epidemiológica, municipio, departamento y conteo de casos.

Adicionalmente, se cuenta con dos bases de datos departamentales: una con el PIB por departamento entre 2005 y 2024, y otra con la población de cada departamento de Colombia en 2020, separándola por rango de edad y sexo. Estas bases permiten contextualizar los incidentes en términos de carga relativa y posibles factores socioeconómicos.

A continuación, exploraremos visualmente algunas tendencias y distribuciones en los datos para comprender mejor este fenómeno de salud pública.

Calidad y cobertura de los datos

Antes de profundizar en patrones temporales y geográficos, es útil revisar indicadores básicos de cobertura del dataset.

Tabla I: Indicadores básicos de cobertura y completitud

Indicador	Valor
Filas	10895
Casos totales	29792
Semanas reportadas	52
Departamentos reportados	34
Municipios reportados	945
% filas con NA	0.00 %

Tabla II: Semanas epidemiológicas con mayor número de casos

SEMANA	casos	participacion
39	698	2.34 %
37	684	2.30 %
44	684	2.30 %
46	675	2.27 %
38	674	2.26 %
45	667	2.24 %

Exploración Temporal: Gráfico de Áreas Apiladas (Stream Chart)

El siguiente gráfico ilustra la evolución temporal de los casos reportados a lo largo de las semanas epidemiológicas de 2021, desglosado por departamento. Este tipo de visualización permite observar cómo cambia el volumen de incidentes en diferentes regiones a lo largo del tiempo.

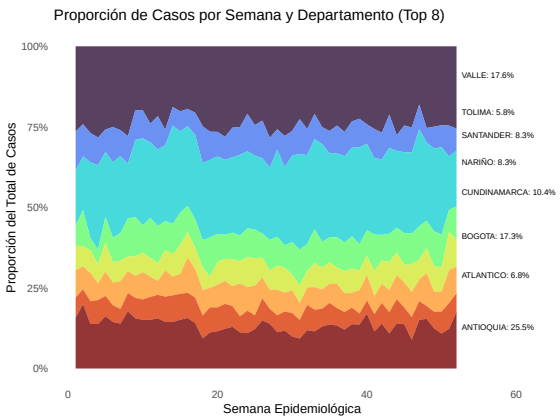

Figura 1: Evolución semanal de casos por departamento

Exploración Geográfica: Gráfico de Dispersión (Scatterplot)

A continuación, presentamos un gráfico de dispersión que muestra la relación entre la variabilidad semanal (desviación estándar de casos) y el volumen total anual de casos por cada departamento. Esto nos ayuda a identificar regiones con altos reportes constantes versus aquellas con picos esporádicos.

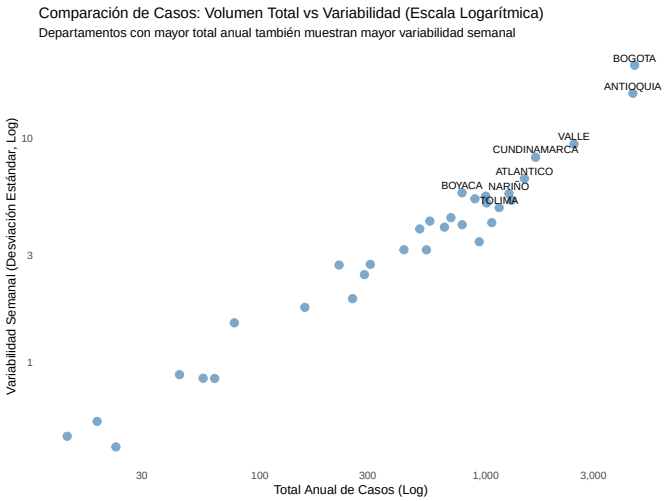

Figura 2: Volumen Total Anual vs Variabilidad Semanal por Departamento

Tendencia temporal semanal (total nacional)

Como en este dataset hay una sola categoría de evento, es más coherente analizar la serie agregada nacional por semana.

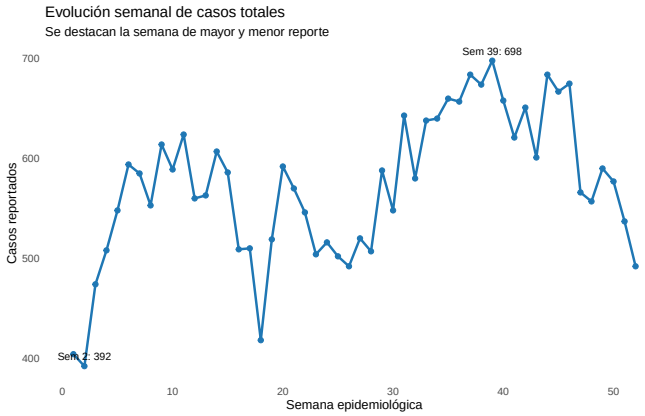

Figura 3: Tendencia semanal de casos totales con puntos clave

Tasa por 100 mil habitantes (ajuste por tamaño poblacional)

El volumen absoluto de casos está influenciado por el tamaño poblacional. Para hacer comparaciones territoriales más justas, se calcula una tasa anual aproximada por cada 100 mil habitantes usando la base poblacional 2020.

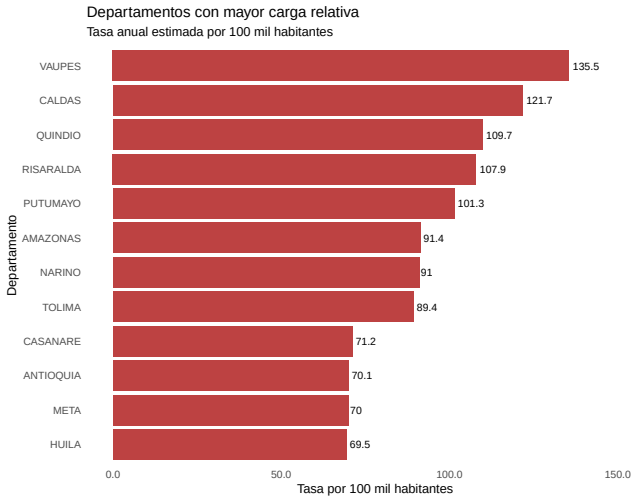

Figura 4: Top 12 departamentos por tasa anual estimada de casos por 100 mil habitantes

Mapa coroplético departamental (tasa per cápita)

Para visualizar la severidad relativa en el territorio, se integra el shapefile oficial departamental y se colorea por tasa anual estimada por 100 mil habitantes.

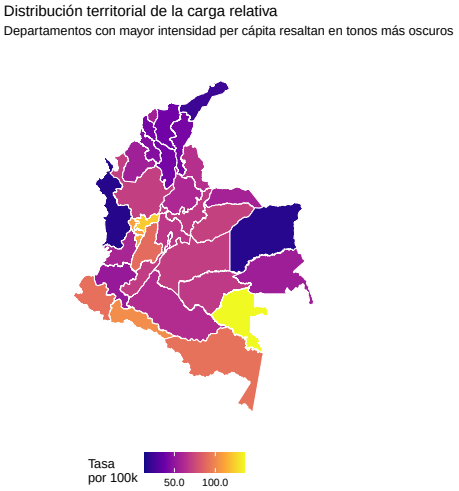

Figura 5: Mapa departamental de tasa anual estimada por 100 mil habitantes

Tabla III: Top 10 por tasa por 100 mil habitantes (tabla de referencia)

departamento	casos	poblacion	tasa_100k
VAUPES	44	32472	135.5
CALDAS	1063	873650	121.7
QUINDIO	565	514847	109.7
RISARALDA	1008	934519	107.9
PUTUMAYO	308	303925	101.3
AMAZONAS	63	68931	91.4
NARINO	1267	1392916	91.0
TOLIMA	1146	1281846	89.4
CASANARE	290	407175	71.2
ANTIOQUIA	4482	6396839	70.1

Conclusiones Preliminares

- Las visualizaciones muestran claras diferencias en los reportes a nivel departamental.
- El *Gráfico de Corriente* evidencia que algunos departamentos mantienen una proporción estable a lo largo de las semanas, mientras que otros muestran ligeras fluctuaciones estacionales.
- Los indicadores de cobertura sugieren una base amplia (52 semanas, 34 unidades departamentales y 945 municipios reportados), útil para análisis descriptivos nacionales.
- La serie por tipo de evento permite identificar si los picos semanales obedecen a un solo fenómeno o a una dinámica compartida entre categorías.
- El ajuste por población cambia el ranking territorial: además de los departamentos con alto volumen absoluto, emergen otros con alta carga relativa por habitante.

Nota: Este análisis es de carácter exploratorio y técnico; requiere interpretación por parte de especialistas en salud pública.